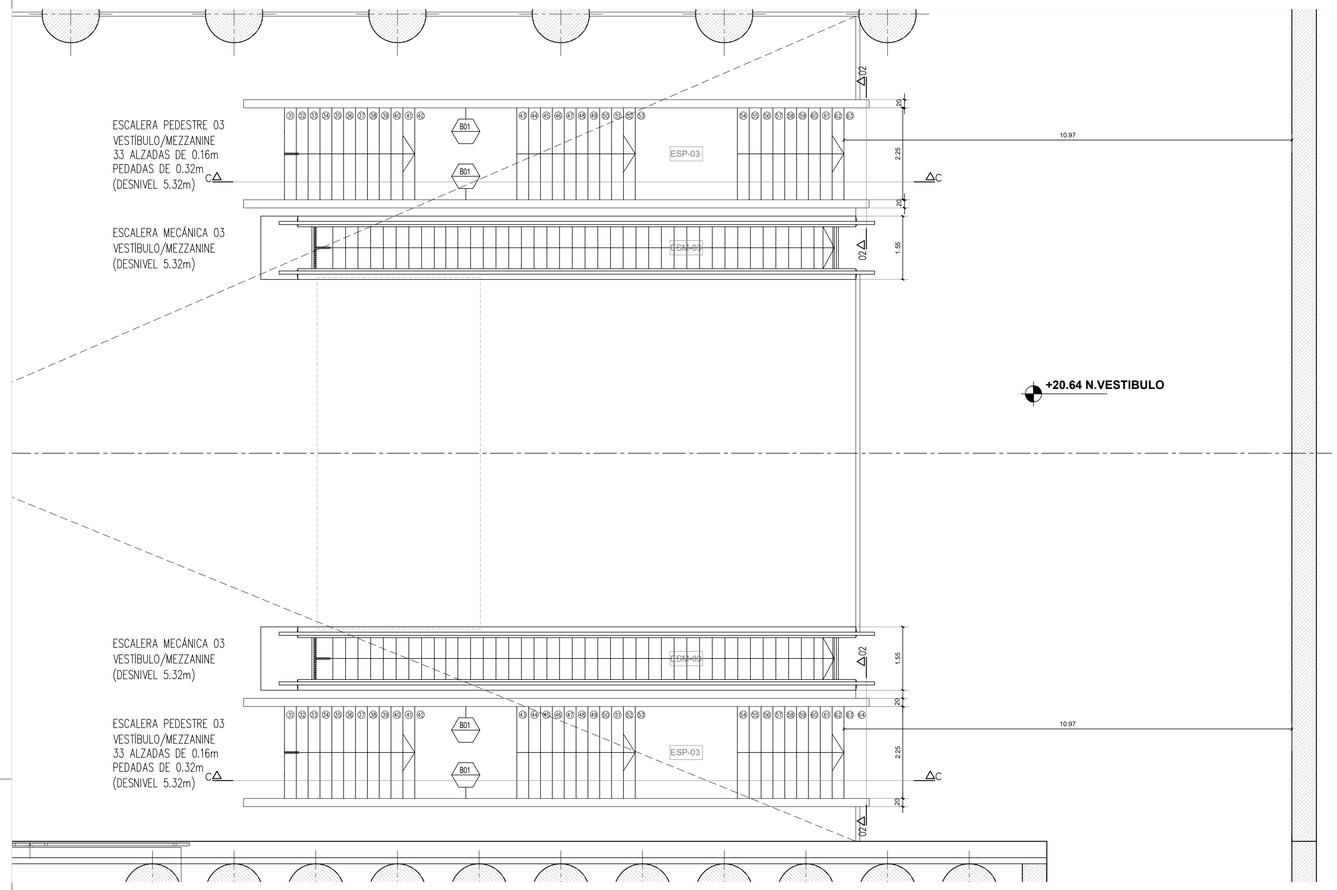
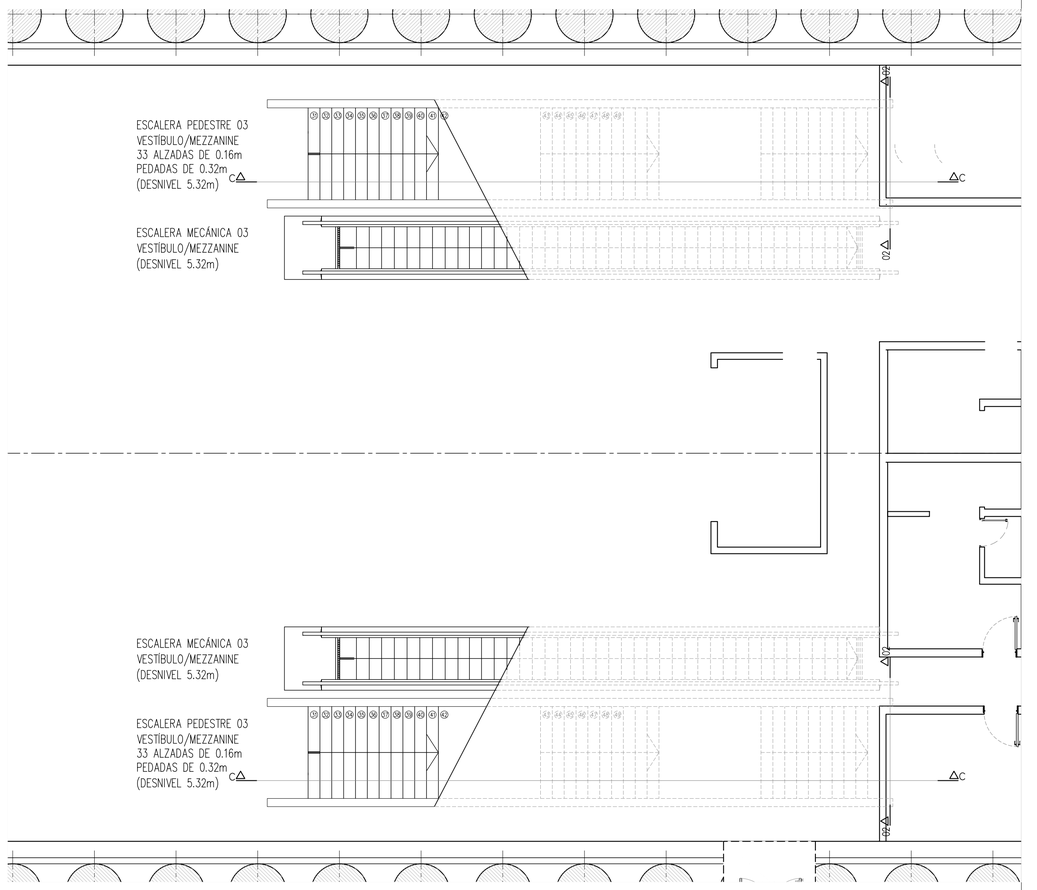
ESCALERA 03 - NIVEL VESTIBULO / NIVEL MEZZANINE

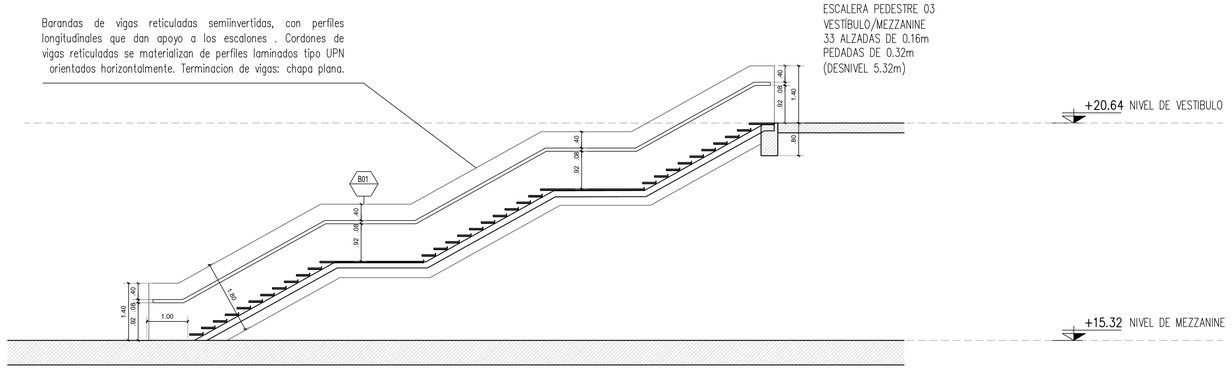
PLANTA NIVEL VESTIBULO 1:75



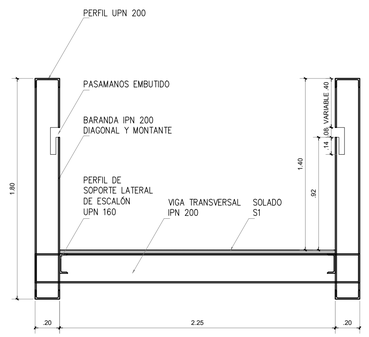
PLANTA NIVEL MEZZANINE 1:75



CORTE C-C 1:75



CORTE DETALLE 02
1:25



NOTACIÓN

LOCAL — INDICA NOMBRE DE LOCAL: NUMERO DE LOCAL
N.N.C. — NIVEL DE PLANTA
CA. 21.00 / SA. 21.75 — CIELORRASO Y ALTURA DEL LOCAL
SOLADO Y ZOCALO
P/D / D/D — INDICA NUMERO DE CARPINTERIA
INDICA ANCHO DE VANO
INDICA DETALLE DE SECTOR O LOCAL
DETALLE 01 VER PLANO A1001
INDICA TIPO DE MURO SEGUN PLANILLA
INDICA TERMINACION MURO SEGUN PLANILLA

MUROS

- M1 — TABIQUE DE HORMIGÓN ARMADO S/ CÁLCULO.
- M2 — TABIQUE DE HORMIGÓN BLANCO A LA VISTA UNA SOLA CARA, ENCOFRADO ENCLOJO TIPO "GRANDES" SELECCIÓN DE PRIMERA CALIDAD CON SEPARADORES A 30 MM, PASADORES MODULADOS S/ PLANO DE ENCOFRADO.
- M3 — TABIQUE COMPUESTO: TABIQUE DE HORMIGÓN ARMADO SEGÚN CÁLCULO ESPESOR VARIABLE + LADRILLO CERÁMICO PORTANTE 12X18X33.
- M4 — TABIQUE DE LADRILLO CERAMANTO HUECO DE 12X18X33.
- M5 — TABIQUE DE LADRILLO CERÁMICO HUECO DE 18X18X33.
- M6 — TABIQUE DE LADRILLO COMÚN 12X25X5 CM REVOCADO + ESTRUCTURA METÁLICA DE CHAPA GALVANIZADA DE 70MM +FIBRA DE VIDRIO (15 MM 35 KG/M3) +SEPARACION DE 3 CM + FIBRA DE VIDRIO (50 MM 35 KG/M3) + PLACAS CEMENTICIAS DE 15 MM. • ESTRUCTURA GALVANIZADA DE 54 MM + FIBRA DE VIDRIO (50 MM 30KG/M3) + CHAPA PERFORADA. SEGÚN CÁLCULO SOBRE BASTIDOR DE ALUMINIO.
- M7 — TABIQUE DE LADRILLO CERÁMICO HUECO DE 8X18X33 + CAMARA DE AIRE 3CM+ REVOQUE.
- M8 — TABIQUE DE LADRILLO CERÁMICO HUECO DE 8X18X33+REVOQUE.
- M9 — TABIQUE DE LADRILLO COMÚN DE 12X25X5, APAREJO DE 15CM + REVOQUE HIDROFUGO + PLACA GRANITICA TIPO TERRAZZO (DEM S1) DE UN LADO.

TERMINACIONES Y REVESTIMIENTOS

- R1 — PLACA GRANITICA TIPO TERRAZZO VIBRADA, PRENSADA Y PULIDA PARA TERMINACIÓN E IMPERMEABILIZACIÓN EN OBRA. TERMINACIÓN SATINADA. MEDIDA NOMINAL 397MM/397MM/15MM (TOLERANCIA +/- 1MM). CANTO RECTIFICADO. ABSORCIÓN DE AGUA 0.7 /MAX 4.50%. COLOR DE MASA, COLOR, GRANULOMETRÍA Y PORCENTAJE DE PIEDRA A DEFINIR SOBRE MUESTRAS.
- R2 — PINTURA SILICONADA HIDRÓFUGA INCOLORA EN BASE ACUOSA "SILEQUIM A" O SIMILAR EQUIVALENTE.
- R3 — G.R.C. (GLASS FIBER REINFORCED CONCRETE) COMPUESTO DE UNA MATRIZ DE MORTERO ARMADO CON FIBRA DE VIDRIO RESISTENTE A LOS ÁLCALIS. SISTEMA TIPO STUD FRAME FORMADO POR UNA CA SCARA DE G.R.C. DE 15 MM A LA QUE SE LE INCORPORA UN BASTIDOR TUBULAR METÁLICO ZINCADO FIJADO MEDIANTE CONECTORES METÁLICOS A DICHA CÁSCARA CON AISLACIÓN DE FIBRA DE VIDRIO TIPO ACUSTIVER P550-70 MM. TIPO PICAST O SIMILAR EQUIVALENTE.
- R4 — G.R.C. CON AISLACIÓN ACÚSTICA: (GLASS FIBER REINFORCED CONCRETE) COMPUESTO DE UNA MATRIZ DE MORTERO ARMADO CON FIBRA DE VIDRIO RESISTENTE A LOS ÁLCALIS. SISTEMA TIPO STUD FRAME FORMADO POR UNA CA SCARA PERFORADA DE G.R.C. DE 15 MM A LA QUE SE LE INCORPORA UN BASTIDOR TUBULAR METÁLICO ZINCADO FIJADO MEDIANTE CONECTORES METÁLICOS A DICHA CÁSCARA TIPO PICAST O SIMILAR EQUIVALENTE. MEDIDA NOMINAL 397MM/397MM/15MM (TOLERANCIA +/- 1MM). CANTO RECTIFICADO. ABSORCIÓN DE AGUA 5.7% (/MAX 4.50%). RESISTENCIA AL DESGASTE 12(/MIN 4/15MM). PRUEBA DE IMPACTO: 180 (/MAX/TOR ALTURA). RESISTENCIA A LA FLEXIÓN: 5MN/CM2(/MIN/MAX/SIN/CM2). COLOR DE MASA, COLOR, GRANULOMETRÍA Y PORCENTAJE DE PIEDRA A DEFINIR SOBRE MUESTRAS.
- R5 — PINTURA AL LATEX ACRÍLICO. TIPO Y COLOR A DEFINIR.
- R6 — ESMALTE SINTÉTICO AL AGUA. TIPO Y COLOR A DEFINIR.
- R7 — PINTURA AL LATEX ACRÍLICO ANTIHONGOS. TIPO Y COLOR A DEFINIR.
- R8 — REVESTIMIENTO GRANITICO CON LIGANTE ACRÍLICO PIEDRA PLAST. DE MOLINOS TARQUINI. COLOR: FINISTERRE BALNEARIA.
- R9 — REVESTIMIENTO ACERO INOXIDABLE PERCHADO.

CIELORRASOS

- C1 — CIELORRASO SUSPENDIDO DE PLACAS DE ROCA DE YESO RESISTENTE A LA HUMEDAD JUNTA TOMADA COMPUESTO POR PLACA DE ROCA DE YESO DE 12.5MM + ESTRUCTURA METALICA DE CHAPA GALVANIZADA N° 24 COMPUESTA POR SOLERAS DE 70 MM Y MONTANTES DE 69 MM SEPARADOS CADA 40 CM. C/ REFUERZO PARA ANTEF. DE ILUMINACIÓN.
- C2 — CIELORRASO SUSPENDIDO DE PLACAS DE ROCA DE YESO JUNTA TOMADA COMPUESTO POR PLACA DE ROCA DE YESO RESISTENTE RF60 DE 12.5MM + ESTRUCTURA METÁLICA DE CHAPA GALVANIZADA N° 24 COMPUESTA POR SOLERAS DE 70 MM Y MONTANTES DE 69 MM SEPARADOS CADA 40 CM. C/ REFUERZO PARA ANTEF. DE ILUMINACIÓN.
- C3 — GRC (GLASS FIBER REINFORCED CONCRETE) COMPUESTO DE MORTERO Y VIDRIO. ESPESOR 10MM SOBRE BASTIDOR METÁLICO ZINCADO SEGÚN CÁLCULO. TIPO PICAST O SIMILAR EQUIVALENTE.
- C4 — PINTURA SILICONADA HIDRÓFUGA INCOLORA EN BASE ACUOSA "SILEQUIM A" O SIMILAR EQUIVALENTE.

ZÓCALOS Y SOLAS

- Z1 — ZÓCALO SANITARIO H:100, RADIO DE CURVATURA:15MM, LARGO: 397MM, ANCHO: 50MM, ESPESOR: 18MM. IDEM S1.
- Z2 — ZÓCALO DE ALISADO DE CEMENTO CON COLOR INCORPORADO H:150MM ESPESOR:15MM.
- SO1 — SOLIA VARILLA ACERO INOXIDABLE "18.9M MARCA ATRIM O SIMILAR EQUIVALENTE.

SOLADOS

- S1 — PLACA GRANITICA TIPO TERRAZZO VIBRADA, PRENSADA Y PULIDA PARA TERMINACIÓN E IMPERMEABILIZACIÓN EN OBRA. TERMINACIÓN SATINADA. MEDIDA NOMINAL 397MM/397MM/15MM (TOLERANCIA +/- 1MM). CANTO RECTIFICADO. ABSORCIÓN DE AGUA: 5.7% (/MAX 4.50%). RESISTENCIA AL DESGASTE: 12(/MIN 4/15MM). PRUEBA DE IMPACTO: 180 (/MAX/TOR ALTURA). RESISTENCIA A LA FLEXIÓN: 5MN/CM2(/MIN/MAX/SIN/CM2). COLOR DE MASA, COLOR, GRANULOMETRÍA Y PORCENTAJE DE PIEDRA A DEFINIR SOBRE MUESTRAS.
- S2 — ESCALÓN GRANÍTICO CONTINUO EJECUTADO IN SITU CON AGREGADO DE FIBRAS DE NYLON SOBRE CARPETA DE CONCRETO PARA TERMINACIÓN. IMPERMEABILIZACIÓN EN OBRA. TERMINACIÓN SATINADA. COLOR DE MASA, COLOR, GRANULOMETRÍA Y PORCENTAJE DE PIEDRA A DEFINIR SOBRE MUESTRAS. ESPESOR COLADO 12MM CON MALLA DE 150X150MM X 6SIGWG.
- S3 — SOLADO DE PREVENCIÓN. PLACA GRANITICA TIPO TERRAZZO VIBRADA, PRENSADA Y PULIDA PARA TERMINACIÓN E IMPERMEABILIZACIÓN EN OBRA. IDEM S1. SUPERFICIE TEXTURADA EN FORMA DE BOTONES EN RELIEVE DE 5MM +/- 1MM DE ALTURA, CON DIAMETRO DE BASE 25MM +/- 5MM. COLOCADOS EN TRESBOLILLO CON UNA SEPARACIÓN ENTRE CENTROS DE LOS RELIEVES DE 65MM +/- 5MM. COLOR DE MASA, COLOR, GRANULOMETRÍA Y PORCENTAJE DE PIEDRA A DEFINIR SOBRE MUESTRAS.
- S4 — SOLADO GUÍA PARA DISCAPACITADOS VISUALES. PLACA GRANÍTICA TIPO TERRAZZO VIBRADA, PRENSADA Y PULIDA PARA TERMINACIÓN E IMPERMEABILIZACIÓN EN OBRA. IDEM S1. SUPERFICIE TEXTURADA EN FORMA DE TIRAS BARRAS EN RELIEVE DE SECCIÓN PRIMABLE TRUNCA SIN ARISTAS VIVAS DE 4MM DE ALTURA POR 35MM MAS 4MM DE BASE SEPARADAS 37MM +/- 5MM. LA LONGITUD DE LAS BARRAS SERÁ DE 35MM. COLOR DE MASA, COLOR, GRANULOMETRÍA Y PORCENTAJE DE PIEDRA A DEFINIR SOBRE MUESTRAS.
- S5 — PLACA GRANÍTICA TIPO TERRAZZO VIBRADA, PRENSADA Y PULIDA PARA TERMINACIÓN E IMPERMEABILIZACIÓN EN OBRA. IDEM S1. SUPERFICIE ANTIDESLIZANTE CONSTITUIDA POR UNA RELIEVE DE CUADRADOS DE 2MM. COLOR DE MASA, COLOR, GRANULOMETRÍA Y PORCENTAJE DE PIEDRA A DEFINIR SOBRE MUESTRAS.
- S6 — ALISADO DE CEMENTO CON COLOR INCORPORADO Y CON ENDURECEDOR CUARCITICO. TERMINACIÓN RODILLADO. COLOR A DEFINIR CON TRATAMIENTO ANTI-POLVO, CURADOR Y SELLADOR TRANSPARENTE SIKAFLOOR CURE HARD 24.
- S7 — VIDRIO LAMINADO TRIPLE CAPA 10+10 +10 CON PVB DE SEGURIDAD SEGÚN CÁLCULO. TERMINACIÓN SUPERFICIAL ANTIDESLIZANTE EN BANDAS EJECUTADO MECÁNICAMENTE POR DESBASTADO EN LA TOTALIDAD DE LA SUPERFICIE DE LA PIEZA.
- S8 — CARPETA ANTIENSUCIANTE TIPO MAT TEK CON SUBSTRATO DE FIBRAS DE POLIPROPILENO DE UNIÓN ENTRE SI POR UNIONES PERPENDICULARES DE PVC Y REVESTIDOS POR TIRAS INTERCAMBIABLES DE REVESTIMIENTO TEXTIL RUGOSO BOUCLÉ, DE POLIPROPILENO DE 40 MICRONES. COLOR NEGRO. ALTURA DE LA CARPETA 18MM.

SOLADO TIPO S3
LOS SOLADOS DE PREVENCIÓN SON SEÑALIZACIONES EN PISOS QUE SE UTILIZAN PARA:
-INDICAR COMIENZO Y FINALIZACIÓN DE UNA FRANJA GUÍA.
-SEÑALAR BIFURCACIONES EN UNA FRANJA GUÍA.
-INDICAR LA PRESENCIA DE OBSTÁCULOS EN LA TRAYECTORIA.
-INFORMAR SOBRE LA EXISTENCIA DE OBSTÁCULOS Y ELEMENTOS DE INFORMACIÓN.
EL SOLADO DE PREVENCIÓN SE COLOCARÁ, SOBRE TODO EL ANCHO, FRENTE DE ESCALERAS Y RAMPAS, EN UNA FRANJA DE 600mm DE LADO COMO MÍNIMO.
TAMBIÉN EL COLOCARÁ EN EL PERÍMETRO DE TODOS LOS BAJO ESCALERAS PERO EN UNA FRANJA DE 300mm.

SOLADO TIPO S4
LAS FRANJAS DE GUÍA PARA DISCAPACITADOS VISUALES SON SEÑALIZACIONES EN SOLADOS QUE INDICAN LA DIRECCIÓN DE RECORRIDO, CUYAS ACANALADURAS SIEMPRE DEBEN ESTAR ORIENTADAS EN LA DIRECCIÓN DE LA MARCHA.
4.2.3 SE DEBEN COLOCAR DENTRO DEL VOLUMEN LIBRE DE RIESGO, SEGÚN IRAM 11100, A UNA DISTANCIA MÍNIMA DE 600mm DE LOS ELEMENTOS FIJOS, EN GRANDES ESPACIOS SIN PAUTAS DE REFERENCIA PRÓXIMAS.

SOLADO TIPO S5
LOS SOLADOS DE RIESGO SON SEÑALIZACIONES EN PISOS QUE SE UTILIZAN PARA:
-ALERTAR SOBRE SITUACIONES DE RIESGO DE CAÍDA POR LA PRESENCIA DE DESNIVELES INFRANQUEABLES, BORDES DE ANDENES, ESCALERAS DESCENDENTES Y EN EL LÍMITE DE ÁREAS RESTRINGIDAS POR SEGURIDAD.
SE DEBEN DISPONER SOLADOS DE PELIGRO EN:
-LOS BORDES DE ANDENES.
EN EL BORDE DE ANDÉN EL SOLADO DE PELIGRO SE COMBINARÁ CON DOS PIEZAS DEL SOLADO DE PREVENCIÓN COMO LO INDICA LA FIGURA

NOTAS: EL PRESENTE PLANO ES INDICATIVO. LA CONTRATISTA CONFECCIONARÁ LOS PLANOS DE DETALLE DEFINITIVO, QUE DEBERÁN SER APROBADOS POR LA D.G.U.BR Y LA DIRECCIÓN DE OBRA. EL PLANO PRESENTADO POR LA CONTRATISTA ESTARÁ EN IR TODO DE ACUERDO CON LA NORMATIVA VIGENTE. TODOS LOS DETALLES CONSTRUCTIVOS DEBAN COORDINADOS Y CONPATIBILIZADOS EN OBRA.

PLANO NO APTO PARA CONSTRUCCIÓN

MODIFICACIONES:

REVISION	FECHA	DESCRIPCION
00	20-11-2025	EMISIÓN PARA LICITACIÓN
01	10-04-2026	EMISIÓN PARA LICITACIÓN

Gobierno de la Ciudad Buenos Aires

MINISTERIO DE INFRAESTRUCTURA
SUBSECRETARIA DE PROYECTOS Y OBRAS
DIRECCION GENERAL DE PROYECTOS

DGPRO

Obra: LÍNEA F			PLANO-2026-23204414-GCABA-SSPO
Plano Estacion Constitución- Detalle Escaleras Acceso Principal 03 de 04			LF-ES-CON-ARQ-PL-026-03-R01
Fecha :10/04/2026	Eq. de Proyecto: UPU - ATEC - IATASA	Dibujó: JS	Revisó: GV / Escala: 1:75 / 1:25

Nº: 026-03

G O B I E R N O DE LA C I U D A D DE B U E N O S A I R E S

"2026 - Año del 30° Aniversario de la sanción de la Constitución de la Ciudad Autónoma de Buenos Aires"

Hoja Adicional de Firmas
Plano

Número: PLANO-2026-23204414-GCABA-SSPO

Buenos Aires, Domingo 17 de Mayo de 2026

Referencia: LF-ES-CON-ARQ-PL-026-03_1

El documento fue importado por el sistema GEDO con un total de 1 pagina/s.

Digitally signed by Comunicaciones Oficiales
Date: 2026.05.17 16:39:21 -03:00

Facundo Lombardo
Subsecretario
SUBSECRETARIA PROYECTOS Y OBRAS
MINISTERIO DE MOVILIDAD E INFRAESTRUCTURA

Digitally signed by Comunicaciones Oficiales
Date: 2026.05.17 16:39:23 -03:00